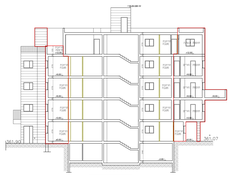

חזית א-ד
קנ"מ 1:100

חזית צפונית
קנ"מ 1:100

חזית מערבית
קנ"מ 1:100

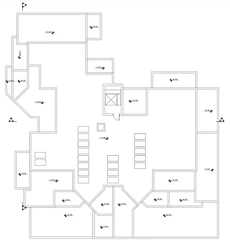

חתכים גגות
מפלס: +14.86 (+376.86)
קנ"מ 1:100

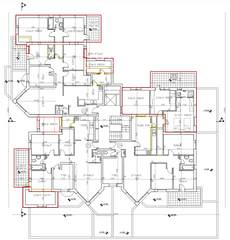

חתכים מפלס ג
מפלס: +9.00 (+371.03)
קנ"מ 1:100

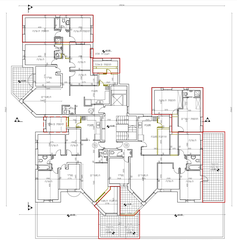

חתכים מפלס א'
מפלס: +3.00 (+365.03)
קנ"מ 1:100

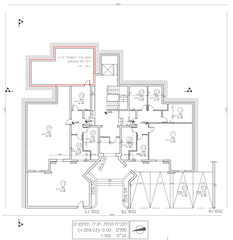

חתכים מפלס ה'ב' כולל מרתף
מפלס: -3.00 (+359.03)
קנ"מ 1:100

חתך ב-ב
קנ"מ 1:100

חזית דרומית
קנ"מ 1:100

חזית מזרחית
קנ"מ 1:100

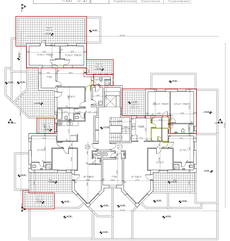

חתכים מפלס ד'
מפלס: +12.00 (+374.03)
קנ"מ 1:100

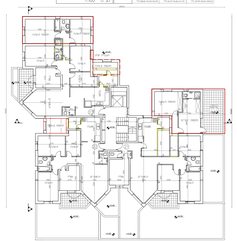

חתכים מפלס ב'
מפלס: +6.00 (+368.03)
קנ"מ 1:100

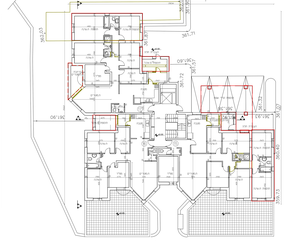

חתכים מפלס טרום
מפלס: +0.00 (+362.03)
קנ"מ 1:100

חישוב שטחים
ק.מ. 1.200

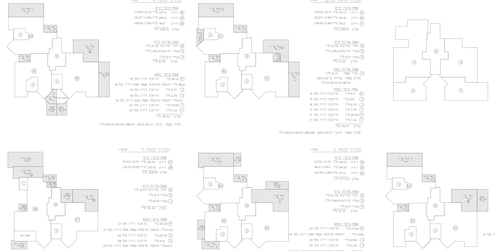

מפלס	עיקרי קיים	עיקרי מוצע	סה"כ עיקרי	שירות קיים	שירות מוצע	סה"כ שירות	סה"כ עיקרי+שירות
-3.00	0.00	0.00	0.00	513.26	0.00	513.26	513.26
0.00	292.91	90.97	383.88	67.8	31.14	98.94	482.82
+3.00	292.91	95.33	388.24	67.8	0.00	67.8	456.04
+6.00	292.91	85.62	378.53	67.8	0.00	67.8	446.33
+9.00	277.67	108.6	386.27	67.8	0.00	67.8	454.07
+12.00	208.94	63.77	272.71	52.49	0.00	52.49	325.2
+14.86	0.00	0.00	0.00	12.37	0.00	12.37	12.37
סה"כ מחתת הקרקעיה	0.00	0.00	0.00	513.26	0.00	513.26	513.26
סה"כ מעל הקרקעיה	1365.34	444.29	1809.63	334.66	31.14	367.2	2176.83
סה"כ כללי	1365.34	444.29	1809.63	849.32	31.14	880.46	2690.09

תכנית מספר
102-0714261

הרחבת דיור
נחל איילון 25,23
נחל נרעם 5,3
רמת בית שמש א'

נספח מס' 3
נחל נרעם 3
קנה מידה 1.100

מקרא:

מוצע

הסגרה

הריסה

תאריך:
27/07/2020